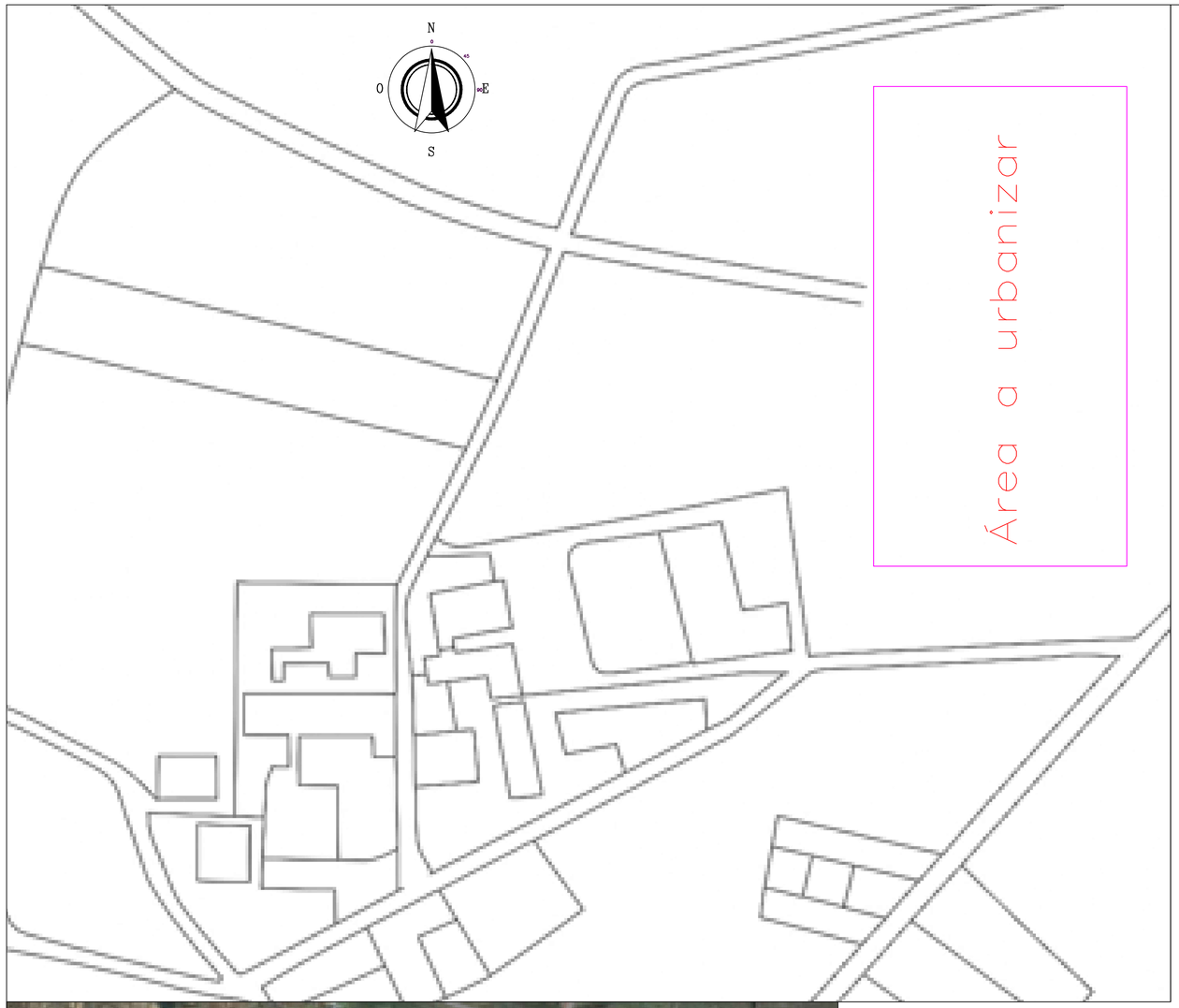

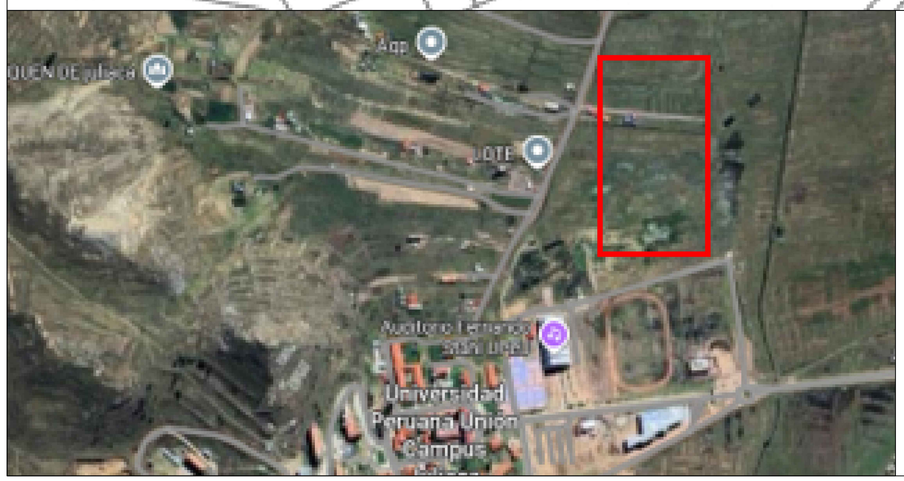

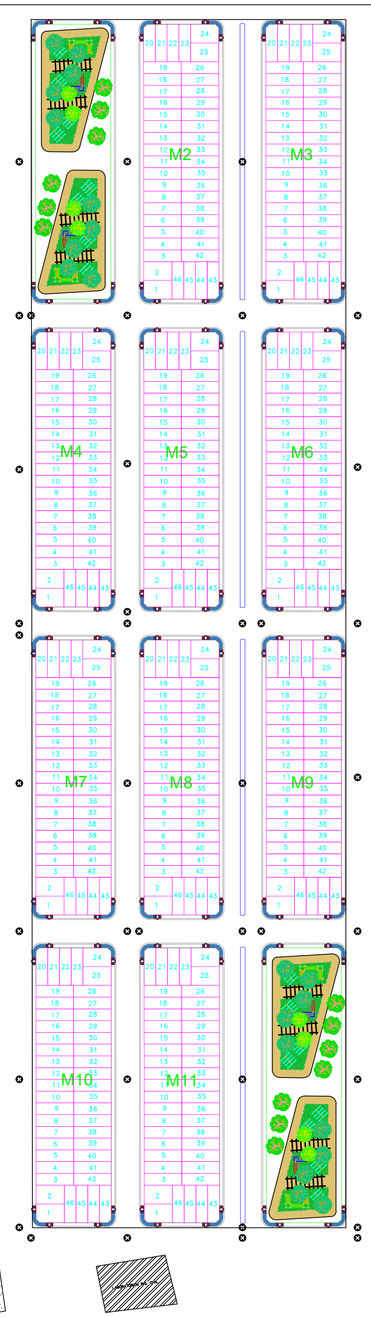

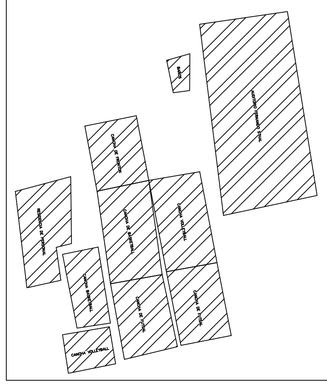

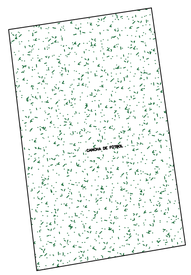

UPeU
UNIVERSIDAD PERUANA UNIÓN

NORTE

Universidad Peruana Unión
Carretera Salida a Arequipa Km. 6
Chullunquiani, Av. Héroes de la
Guerra del Pacífico, Juliaca,
COORDENADAS:
Geograficas: 15°30'48"s–70°11'03"w
Utm: 372891.5,E–8284566.5,N 3888.4,Z



LEYENDA

- Área a urbanizar
- Numeración de manzanas M1–M2–M3
- construcciones existentes
- Número de lotización 1–2–3–4–5
- Futuros buzones para red de alcantarillado
- Lozas deportivas
- Campo deportivo
- Áreas verdes

Presentado por:
- Trujillo Pajsi Alexis Romario
- Chambi Mamani Jhon Elvis
- Vilca Machaca Arnaldo
- Vargas Patiño Sebastian
- Hilasaca Barrios Kevin Samuel
- Nuñez Ochoa Kevin Anderson

Departamento: PUNO
Provincia: SAN ROMAN
Distrito: JULIACA

Facultad: INGENIERÍA Y ARQUITECTURA
E.p: INGENIERÍA CIVIL
Curso: AGUA POTABLE Y SANEAMIENTO
Ciclo: VIII - G3

PROYECTO:
ABASTECIMIENTO DE AGUA POTABLE Y ALCANTARILLADO SANITARIO AL MARGEN IZQUIERDO DE LA UNIVERSIDAD PERUANA UNIÓN, SEDE JULIACA, SAN ROMÁN – PUNO

CONTIENE:
PLANO DE LOTIZACIÓN DEL PROYECTO

Escala grafica:
0 20 40 60 80 100

1: 2000

MTS

20 DE NOV 2025

02