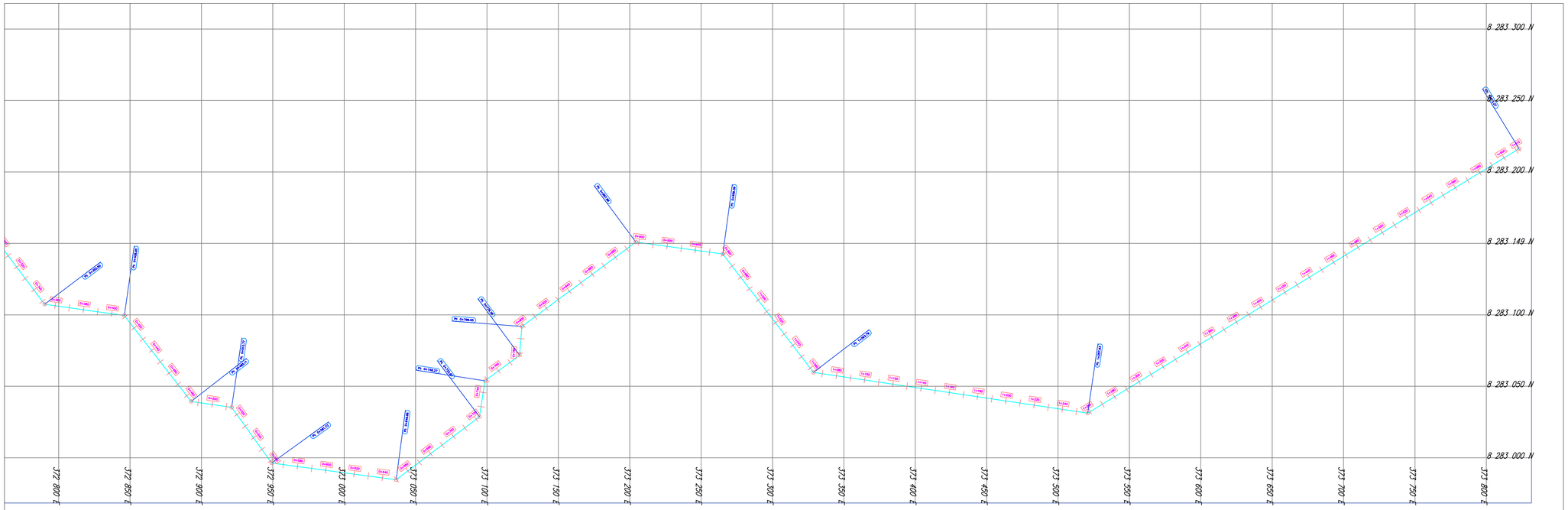

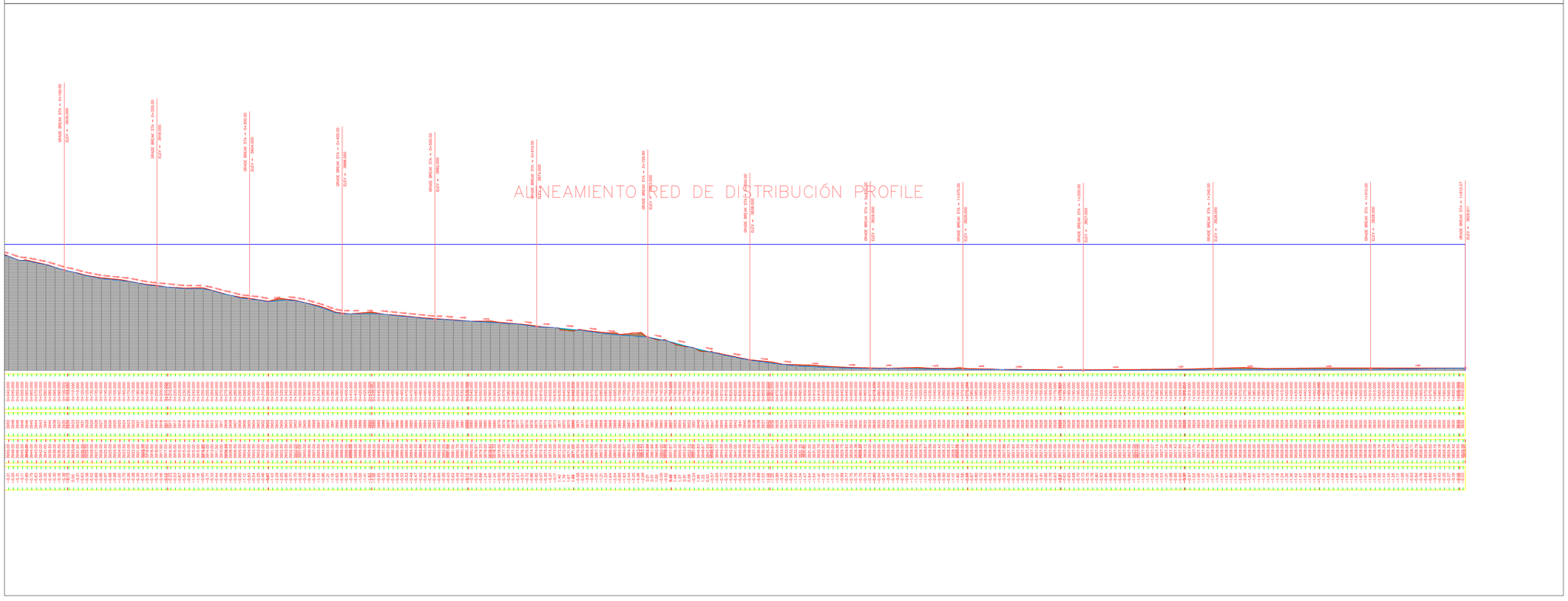

UPeU
UNIVERSIDAD PERUANA UNIÓN

NORTE

Universidad Peruana Unión
Carretera Salida a Arequipa Km. 6
Chullunquiani, Av. Héroes de la
Guerra del Pacífico, Juliaca.
COORDENADAS:
Geograficas: 15°30'48"s–70°11'03"w
Utm: 372891.5,E–8284566.5,N 3888.4,Z

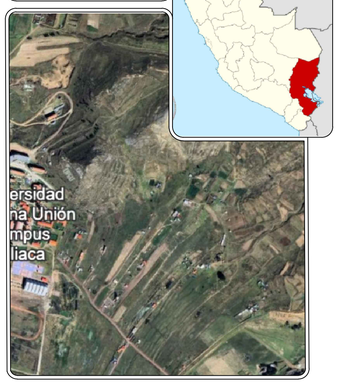

LEYENDA

- ÁREA DE CORTE
- ÁREA DE RELLENO
- ABCISAS
- LÍNEA DE CONDUCCIÓN
- PUNTOS DE CONTROL

Presentado por:
- Trujillo Pajsi Alexis Romario
- Chambi Mamani Jhon Elvis
- Vilca Machaca Arnaldo
- Vargas Patiño Sebastian
- Hilasaca Barrios Kevin Samuel
- Nuñez Ochoa Kevin Anderson

Departamento: PUNO
Provincia: SAN ROMAN
Distrito: JULIACA

Facultad: INGENIERÍA Y ARQUITECTURA
E.p: INGENIERÍA CIVIL
Curso: AGUA POTABLE Y SANEAMIENTO
Ciclo: VIII - G3

PROYECTO:
ABASTECIMIENTO DE AGUA POTABLE A ESPALDAS DE LA UNIVERSIDAD PERUANA UNIÓN, SEDE JULIACA, SAN ROMÁN – PUNO

CONTIENE:
SEGUNDO TRAMO DE PERFIL LONGITUDINAL DE RED DE DISTR.

Escala grafica:
0 18 90 180 270 360

1: 2000

MTS

25 DE NOV 2025

06