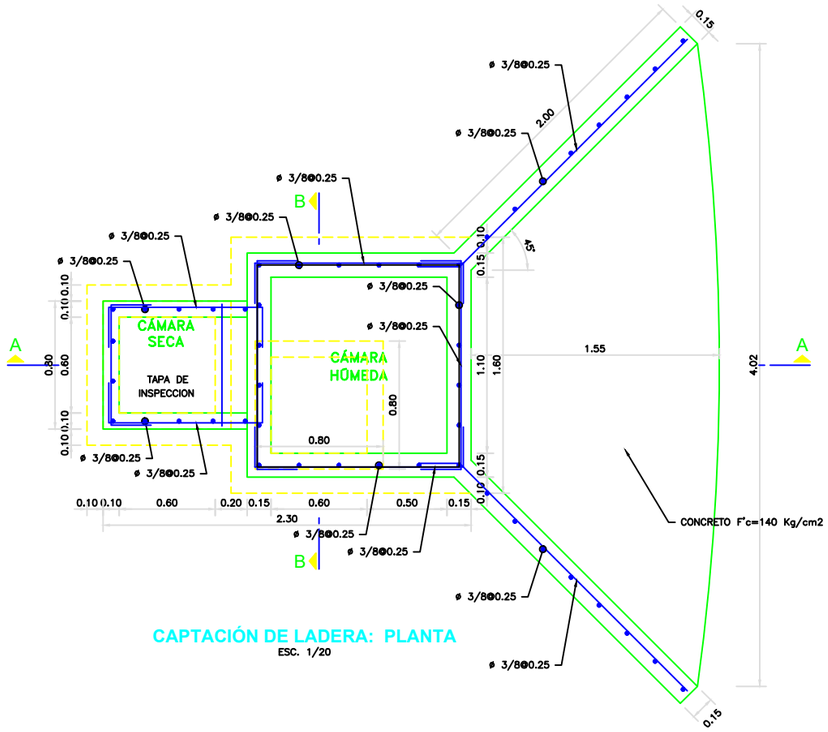

CAPTACIÓN DE LADERA: PLANTA

ESC. 1/20

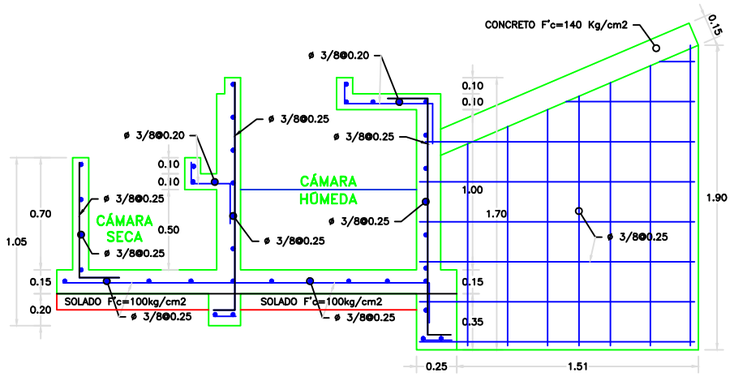

CAPTACIÓN DE LADERA: CORTE A-A

ESC. 1/20

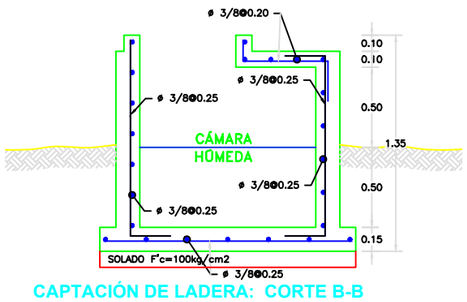

CAPTACIÓN DE LADERA: CORTE B-B

ESC. 1/20

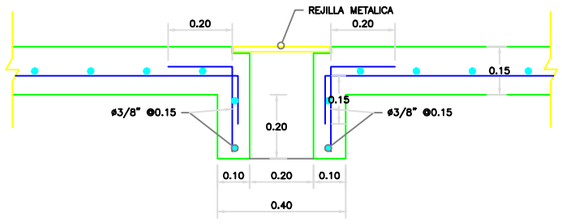

ARMADURA EN SUMIDERO

ESC: 1/10

ESPECIFICACIONES TÉCNICAS

CONCRETO SIMPLE:

- SOLADO — f'c= 10 MPa (100Kg/cm2)

CONCRETO ARMADO:

- EN CERCO MALLA — f'c= 175Kg/cm2
- EN GENERAL — f'c= 20 MPa (210Kg/cm2)
- ESTRUCTURAS EN CONTACTO CON EL AGUA — f'c= 27 MPa (280Kg/cm2)

CEMENTO

- EN GENERAL — Cemento Portland Tipo I
- ESTRUCTURAS EN CONTACTO CON EL SUELO — Revisar las recomendaciones que Indica el Estudio de Suelos

ACERO DE REFUERZO:

- ACERO EN GENERAL — fy=4200 Kg/cm2

EMPALMES TRASLAPADOS:

- ø3/8" : 50
- ø1/2" : 60
- ø5/8" : 75
- ø3/4" : 90

RECUBRIMIENTOS:

- MURO CARA SECA — 0.04 m
- MURO CARA HUMEDA — 0.05 m
- LOSA DE TECHO — 0.03 m
- LOSA DE FONDO — 0.04 m

REVESTIMIENTO PARA SUPERFICIES EN CONTACTO CON EL AGUA:

- TARRAJEO FROTACHADO — C:A, 1:4 e=25 mm
- TARRAJEO CON IMPERMEABILIZADO — C:A, 1:3+SDITV. IMP. e=20 mm

CAPACIDAD PORTANTE:

- q a TERRENO = 0,8 Kg/cm2

EMPALMES POR TRASLAPE

NOTA: NO EMPALMAR MAS DEL 50% EN UNA MISMA SECCION

ø	L
3/8"	50mm
1/2"	60mm
5/8"	75mm
3/4"	90mm

DETALLES TIPICOS DE ESTRIBOS

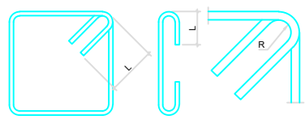

ø	L	Rmin
6mm	10cm	1,5cm.
3/8"	15cm	2,0cm.

NOTAS:

1. EL CONSULTOR DEBE CONSIDERAR ESTA INFORMACIÓN COMO UNA GUÍA, CUYOS CRITERIOS DE DISEÑO DEBEN SER VALIDADOS CON LAS CONDICIONES DEL ÁREA DEL PROYECTO A DESARROLLAR, EN EL CASO DE ENCONTRARSE CON SITUACIONES DIFERENTES EL CONSULTOR DEBERÁ EVALUAR Y PROPONER EL DISEÑO MAS CONVENIENTE.

UPeU UNIVERSIDAD PERUANA UNIÓN

NORTE

Universidad Peruana Unión
Carretera Salida a Arequipa Km. 6
Chulluquiani, Av. Héroes de la Guerra del Pacífico, Juliaca.
COORDENADAS:
Geograficas: 15°30'48"s—70°11'03"w
Utm: 372891.5,E—8284566.5,N 3888.4,Z

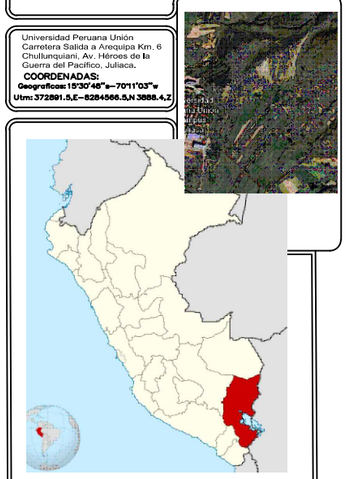

NOTAS

1.– TODAS LAS DIMENSIONES ESTAN EN METROS, SALVO INDICADO.

2.– LA ESCALA GRÁFICA CORRESPONDE AL FORMATO A1

3.– VER TRAZO Y REPLANTEO EN PLANO DE ARQUITECTURA

4.– EL REFUERZO CONTINUA A TRAVES DE LAS JUNTAS DE CONSTRUCCION, DEL TERRENO MEDIANTE EL ESTUDIO DE SUELOS.

5.– PARA EL DISEÑO DEFINITIVO SE TIENE QUE VERIFICAR LA CAPACIDAD PORTANTE DEL TERRENO MEDIANTE EL ESTUDIO DE SUELOS

Presentado por:
- Trujillo Pajsi Alexis Romario
- Chambi Mamani Jhon Elvis
- Vilca Machaca Arnaldo
- Vargas Patiño Sebastian
- Hilasaca Barrios Kevin Samuel
- Nuñez Ochoa Kevin Anderson

Departamento: PUNO
Provincia: SAN ROMAN
Distrito: JULIACA

Facultad: INGENIERÍA Y ARQUITECTURA
E.p: INGENIERÍA CIVIL
Curso: AGUA POTABLE Y SANEAMIENTO
Ciclo: VIII - G3

PROYECTO:
ABASTECIMIENTO DE AGUA POTABLE Y ALCANTARILLADO SANITARIO AL MARGEN IZQUIERDO DE LA UNIVERSIDAD PERUANA UNIÓN, SEDE JULIACA, SAN ROMÁN - PUNO

CONTIENE:
PLANO DE CAPTACIÓN - ESTRUCTURAS

Escala grafica: 0 15 30 45 60 75

1: 1500

MTS

25 DE NOV 2025

13