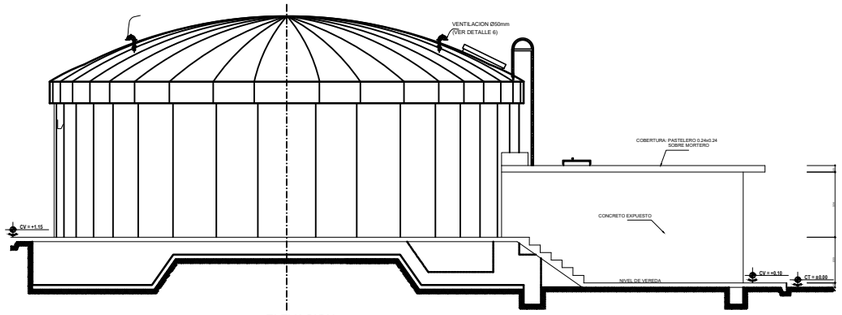

ELEVACION
ESCALA: 1/50

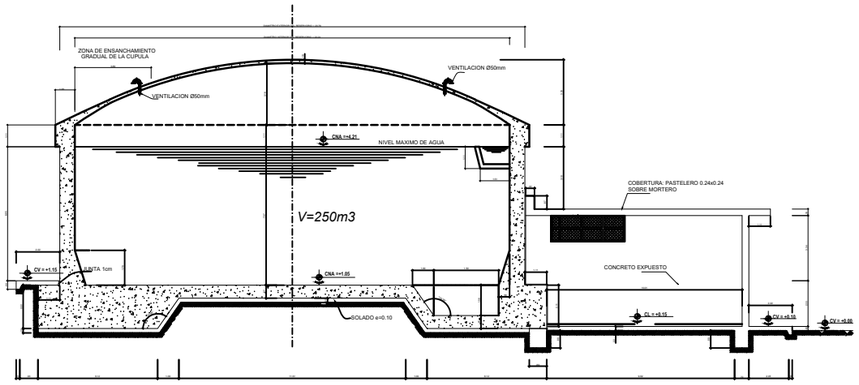

SECCION X-X
ESCALA: 1/50

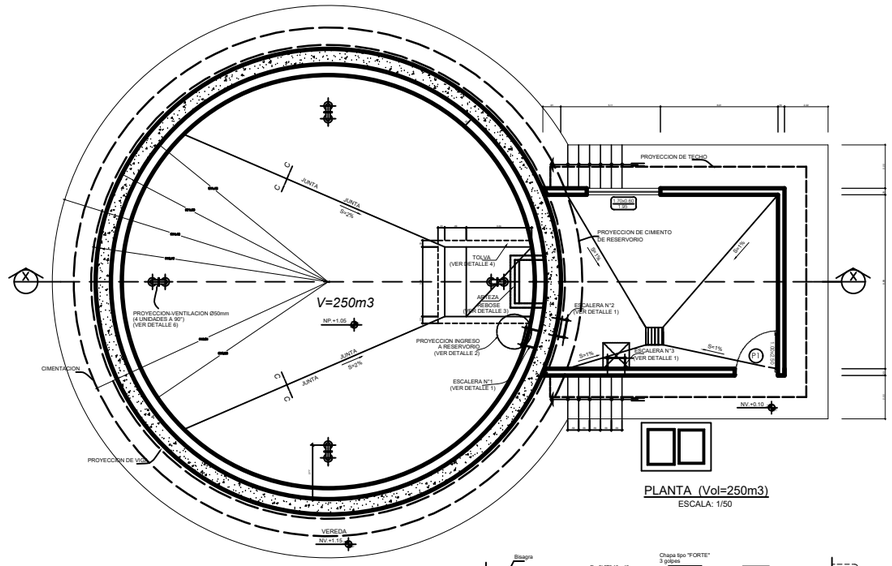

PLANTA (Vol=250m3)
ESCALA: 1/50

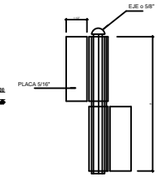

DETALLE TIPICO DE BISAGRA
ESCALA: S/E

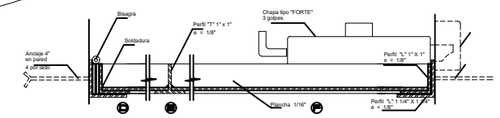

SECCION HORIZONTAL DE P-1
ESCALA: 1/2

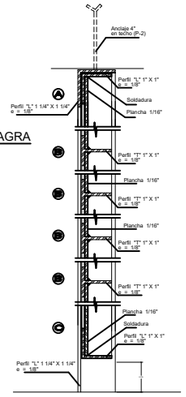

SECCION VERTICAL DE P-1
ESCALA: 1/2

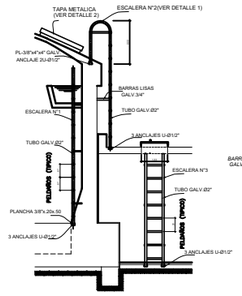

SECCION 1-1
ELEVACION-ESCALERA N°1 - N°2 y N°3
ESCALA: 1/50

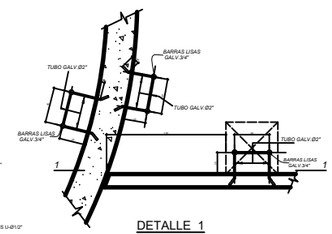

DETALLE 1
ESCALA: 1/25

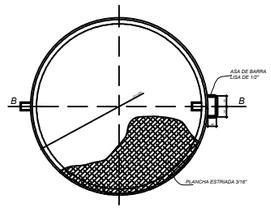

DETALLE 2
PLANTA-TAPA METALICA
ESCALA: S/E

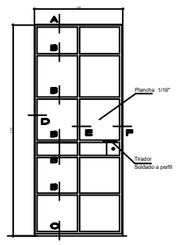

PUERTA P-1
ESCALA: 1/25

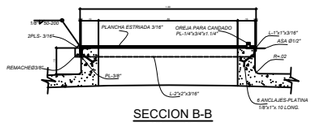

SECCION B-B
ESCALA: S/E

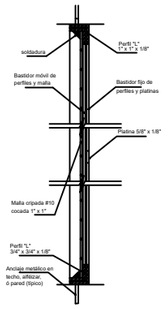

SECCION HORIZONTAL
O VERTICAL DE VENTANA
ESCALA: 1/5

UPeU
UNIVERSIDAD PERUANA UNIÓN

NORTE

Universidad Peruana Unión
Carretera Salida a Arequipa Km. 6
Chullunquiani, Av. Héroes de la
Guerra del Pacífico, Juliaca.
COORDENADAS:
Geográficas 15°30'48"s–70°11'03"w
Utm: 372891.5,E–8284566.5,N 3898.4,Z



ESPECIFICACIONES

MATERIALES
ACERO fy=4200 kg/cm2
Solado: f'c= 100 kg/cm2
Sobrepisos: (con 30% de piedra desplazadora de 0.25 max.) f'c=100 kg/cm2
Fondo y Paredes Reservorio: f'c=240 kg/cm2
Cobertura Reservorio f'c=240 kg/cm2
Caseta de Válvulas: f'c=175 kg/cm2
CEMENTO PORTLAND TIPO II PARA TODO CONCRETO EN CONTACTO CON EL SUELO
CEMENTO PORTLAND TIPO I PARA EL RESTO DE LA ESTRUCTURA

RECUBRIMIENTOS
Concreto vaciado contra el suelo — *7.5 cm.*
Concreto en contacto con el terreno (vaciado con encofrado) — *4.0 cm.*
Cobertura superior de Cúpula — *2.0 cm.*
Fondos, Paredes de Cuba y Vigas de Amarre — *4.0 cm.*

REVOQUES
"IMPERMEABILIZAR LAS SUPERFICIES EN CONTACTO CON EL AGUA CON MEZCLA 1:3 CIA DE 2 cm DE ESPESOR, ACABADO FROTACHADO FINO, UTILIZAR IMPERMEABILIZANTE (SIKA 1 ó SIMILAR) DE ACUERDO A LAS RECOMENDACIONES DEL FABRICANTE.

Presentado por:
- Trujillo Pajsi Alexis Romario
- Chambi Mamani Jhon Elvis
- Vilca Machaca Arnaldo
- Vargas Patiño Sebastian
- Hilasaca Barrios Kevin Samuel
- Nuñez Ochoa Kevin Anderson

Departamento: PUNO
Provincia: SAN ROMAN
Distrito: JULIACA

Facultad: INGENIERÍA Y ARQUITECTURA
E.p: INGENIERÍA CIVIL
Curso: AGUA POTABLE Y SANEAMIENTO
Ciclo: VIII - G3

PROYECTO:
ABASTECIMIENTO DE AGUA POTABLE Y ALCANTARILLADO SANITARIO AL MARGEN IZQUIERDO DE LA UNIVERSIDAD PERUANA UNIÓN, SEDE JULIACA, SAN ROMÁN – PUNO

CONTIENE:
PLANO DE RESERVORIO

Escala grafica:
0 15 30 45 60 75

1: 1500

MTS

25 DE NOV 2025

16